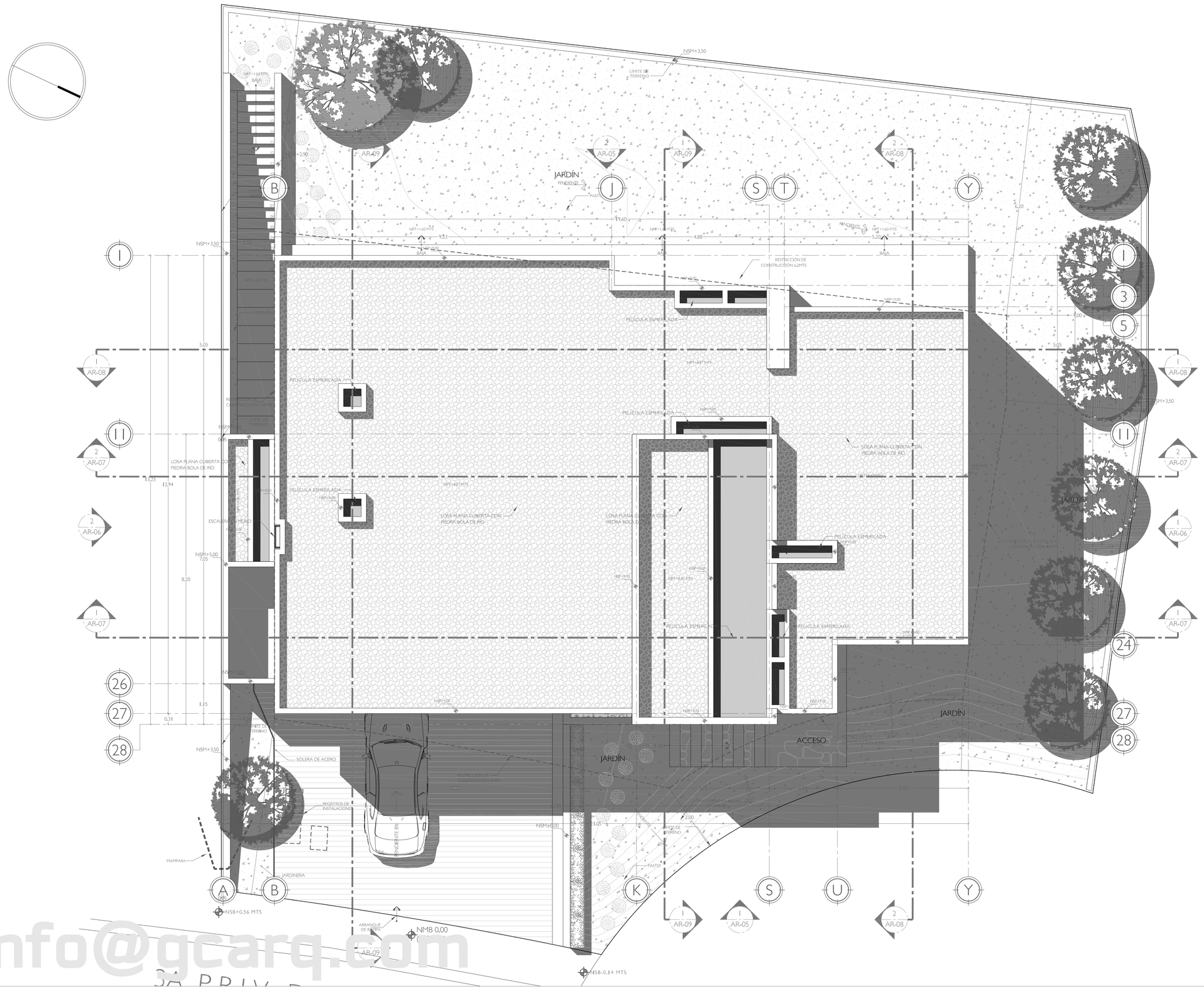

info@gcarq.com

NORTE

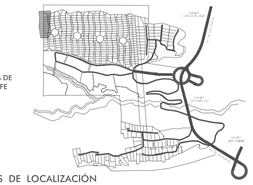

CROQUIS DE LOCALIZACIÓN

CROQUIS DE UBICACIÓN

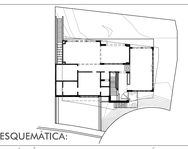

PLANTA ESQUEMÁTICA:

CORTE ESQUEMÁTICO:

SIMBOLOGÍA

NPT: NIVEL DE PISO TERMINADO

NOTAS IMPORTANTES

SUPERFICIE DE TERRENO 580.00 M²
SUPERFICIE DE DESPLANTE 255.94 M² (44.12%)
SUPERFICIE DE JARDÍN 238.63 M² (41.71%)
SUPERFICIE DE PAVIMENTOS 85.43 M² (14.17%)

ÁREAS DE CONSTRUCCIÓN

PLANTA DE SÓTANO = 247.99 M²
PLANTA BAJA = 233.52 M²
PLANTA ALTA = 236.30 M²
ÁREA TOTAL = 717.81 M²

NOTAS GENERALES

RESUMEN NIVEL 1

DESLEGACIONES:

ÁLVARO OBREGÓN
CUAJIMALPA DE MORELOS

CORRESPONSABLES

NO.	REGISTRO	NOMBRE
1	DRO	
2	ESTRUCTURA	
3	INSTALACIONES	
4		

DESARROLLADOR

CUMBRES DE SANTA FE

FIDEICOMISO
CUMBRES DE SANTA FE

PROYECTO:

CASA HABITACIÓN

PLANO:

ARQUITECTÓNICO
PLANTA DE AZOTEA

DISEÑO Y DIRECCIÓN GENERAL:
ARQ. GUILLERMO CAMPOS LOERA
UBICACIÓN:
GUILLERMO GONZÁLEZ CAMARENA 1600
COL. SANTA FE DEL. ÁLVARO OBREGÓN
MÉXICO, DISTRITO FEDERAL C.P. 01210
E-MAIL:
INFO@GCARQ.COM.
COORDINADOR DE PROYECTO:
ARQ. VÍCTOR RENÉ ASTORGA G.

PROPIETARIO:

YUNEL CESIN
MIKE RUIZ

PLANO Nº 06

AR-04

UBICACIÓN:

LOTE 8
AV. DE LOS POETAS Nº 100, MANZ. CD3-8

ESCALA	1:50
ACOTACIÓN	METROS
REVISÓ	
V.O. BO.	
FECHA	FEBRERO DEL 2018

ESCALA GRÁFICA:

0.00 0.50 1.00 2.00 5.00 MTS.
0.25 0.75 1.50 2.50

ARQUITECTOS